الجمهورية التونسية
ولاية صفاقس

دليل المستخدم
لوحة متابعة أنشطة النظافة
بلديات ولاية صفاقس

تدخلات رفع النقاط السوداء ومعالجة المصبات العشوائية

30- 31 مارس2026

- الإعداد :حمزة ينطيف / سهام الرابسيAPI v1.0
الإشراف :والي صفاقس محمد الحجري
التنسيق :كاتب عام ولاية صفاقس، مجد الدين جوادي

المحتويات فهرس

1- نظرة عامة على لوحة المتابعة
2- واجهة لوحة المتابعة الرئيسية
1.2- مؤشرات الأداء الرئيسية (KPIs)
2.2- التنقل بين الأقسام
3- قسم إحصائيات البلاغات
1.3- عدادات الحالة
2.3- البلاغات حسب الخطورة
3.3- البلاغات حسب البلدية
4- قسم البلديات
1.4- بطاقة تفصيلية للبلدية
5- قسم إدارة البلاغات
6- الإبلاغ عن نقطة سوداء
7- الأسئلة الشائعة

1.نظرة عامة على لوحة المتابعة

لوحة متابعة أنشطة النظافة هي منصة رقمية متكاملة مخصصة لمتابعة وتتبع تدخلات رفع النقاط السوداء ومعالجة المصبات العشوائية عبر بلديات ولاية صفاقس.

تُتيح هذه اللوحة لمسؤولي الولاية والبلديات الاطلاع الفوري على مؤشرات الأداء، وتتبع البلاغات المقدمة من المواطنين، وقياس الكميات المرفوعة في كل منطقة.

الأهداف الرئيسية للمنصة

- رصد الكميات المرفوعة من النقاط السوداء والمصبات العشوائية في الوقت الفعلي
- تتبع البلاغات المقدمة من المواطنين وإدارة حالاتها
- مقارنة أداء البلديات الـ 23 عبر الولاية
- تمكين المواطنين من الإبلاغ عن نقاط سوداء جديدة مباشرةً
- تقديم إحصاءات تفصيلية حسب الخطورة والموقع الجغرافي

اسم النظام	لوحة متابعة أنشطة النظافة
نطاق العمل	ولاية صفاقس 23 – بلدية
الفترة المرصودة	مارس2026
إصدار الـAPI	v1.0
الجهة المشرفة	والي صفاقس

2.واجهة لوحة المتابعة الرئيسية

تُعرض عند فتح اللوحة الشاشة الرئيسية التي تحتوي على أهم مؤشرات الأداء، مع شريط تنقل علوي للوصول إلى الأقسام المختلفة.

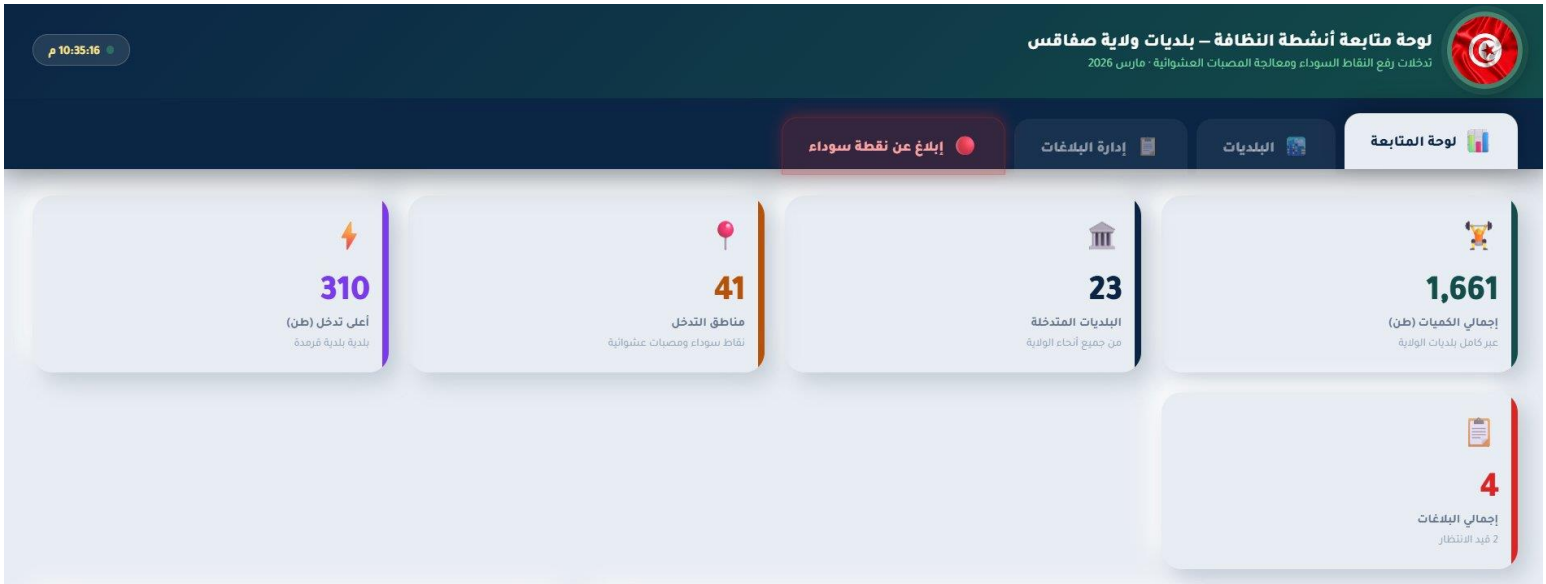

الشكل 1 – لوحة المتابعة الرئيسية مؤشرات الرئيسية الأداء

2.1مؤشرات الأداء الرئيسية(KPIs)

تعرض الشاشة الرئيسية أربعة مؤشرات أداء رئيسية بشكل بطاقات واضحة:

الوصف	المؤشر	اللون
مجموع الكميات المرفوعة عبر جميع بلديات الولاية 1,661 طن	**إجمالي الكميات) طن(**	أصفر □
عدد البلديات التي قامت بتدخلات 23 بلدية	**البلديات المتدخلة**	رمادي □
عدد النقاط السوداء والمصبات المعالجة 41 منطقة	**مناطق التدخل**	برتقالي □
البلدية ذات أعلى كمية مرفوعة 310 طن – بلدية قرمدة	**أعلى تدخل (طن)**	بنفسجي ⚡
إجمالي بلاغات المواطنين 4 بلاغات، 2 قيد الانتظار	**إجمالي البلاغات**	أحمر □

2.2التنقل بين الأقسام

يوجد في أعلى الشاشة شريط تنقل يحتوي على أربعة أقسام رئيسية:

- لوحة المتابعة :الشاشة الرئيسية مع المؤشرات العامة
- البلديات :عرض تفصيلي لكل بلدية على حدة
- إدارة البلاغات :قائمة البلاغات المقدمة مع حالاتها
- إبلاغ عن نقطة سوداء :نموذج تقديم بلاغ جديد - متاح للمواطنين

3.قسم إحصائيات البلاغات

يعرض هذا القسم إحصاءات مفصلة حول البلاغات المقدمة من المواطنين، مع تصنيفها حسب الحالة والخطورة والبلدية.

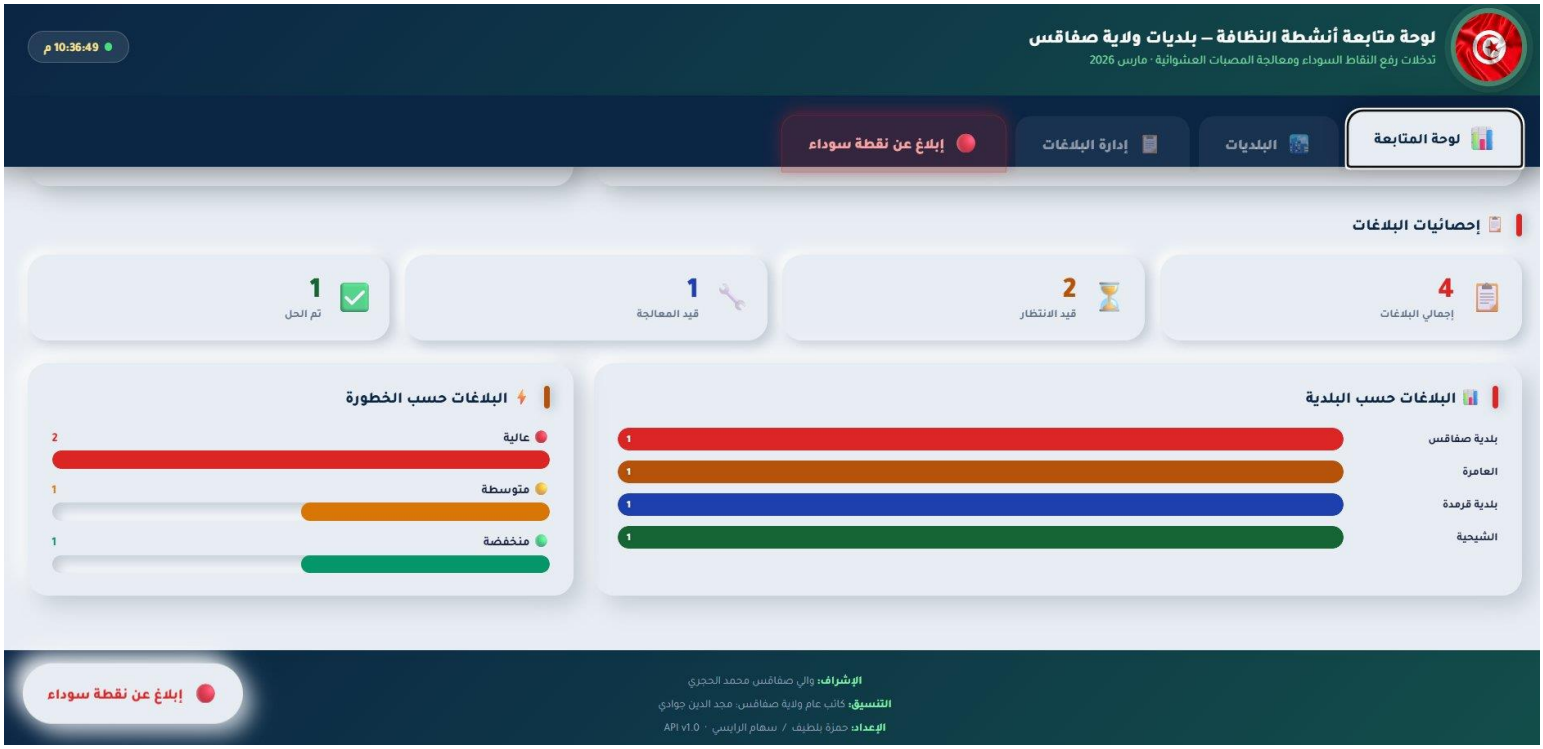

الشكل 2 – قسم إحصائيات البلاغات

3.1عدادات الحالة

تُعرض في الجزء العلوي أربعة عدادات توضح حالة البلاغات:

- إجمالي البلاغات :العدد الكلي للبلاغات المستلمة(4)
- قيد الانتظار :البلاغات التي لم تُعالج بعد(2)
- قيد المعالجة :البلاغات الجاري العمل عليها(1)
- تم الحل :البلاغات التي تمت معالجتها وإغلاقها(1)

3.2 الخطورة حسب البلاغات

يعرض مخطط شريطي ملون توزيع البلاغات حسب درجة الخطورة:

- عالية) أحمر :(تتطلب تدخلاً فورياً 2 – بلاغات
- متوسطة) برتقالي :(تتطلب متابعة قريبة 1 – بلاغ
- منخفضة) أخضر :(يمكن جدولة المعالجة 1 – بلاغ

3.3البلاغات حسب البلدية

يعرض مخطط شريطي أفقي توزيع البلاغات حسب البلدية، مما يتيح تحديد البلديات الأكثر نشاطاً أو التي تحتاج إلى دعم إضافي:

- بلدية صفاقس :بلاغ واحد- أحمر
- العامرة :بلاغ واحد - برتقالي
- بلدية قرمدة :بلاغ واحد- أزرق
- الشيحية :بلاغ واحد - أخضر

نصيحة :كلما كان الشريط أطول، كان عدد البلاغات من تلك البلدية أكبر .استخدم هذا المخطط لتحديد أولويات التدخل الميداني.

4.قسم البلديات

يتيح هذا القسم الاطلاع على قائمة البلديات الـ 23 الممثلة في الولاية، مع بيانات تفصيلية لكل بلدية.

4.1بطاقة تفصيلية للبلدية

بالنقر على أي بلدية تظهر نافذة منبثقة تحتوي على المعلومات التالية:

الشكل 3 – نافذة التفاصيل التفصيلية لبلدية قرمدة

عدد المناطق	عدد نقاط التدخل) النقاط السوداء والمصبات (في هذه البلدية
إجمالي الكميات) طن(	مجموع الكميات المرفوعة بالطن خلال الفترة
الترتيب من حيث الكمية	ترتيب البلدية مقارنةً بباقي البلديات في الولاية
إجمالي البلاغات	عدد البلاغات المقدمة من مواطني هذه البلدية
قيد الانتظار	البلاغات التي لم تُعالج بعد
قيد المعالجة	البلاغات الجاري العمل عليها حالياً
تم الحل	البلاغات المغلقة بعد معالجتها

نصيحة :تحتل بلدية قرمدة المرتبة الأولى من حيث الكميات المرفوعة بـ 310 طن في 3 مناطق، مما يجعلها الأكثر تدخلاً على مستوى الولاية.

5.قسم إدارة البلاغات

يتيح هذا القسم لمسؤولي الولاية والبلديات إدارة البلاغات المقدمة من المواطنين، ومتابعة حالتها من لحظة استلامها حتى الحل.

مراحل حياة البلاغ

1. قيد الانتظار :البلاغ مستلم ولم يُوزع بعد على الفريق المختص
2. قيد المعالجة :الفريق يعمل على معالجة البلاغ ميدانياً
3. تم الحل :المشكلة عولجت وأُغلق البلاغ بنجاح

إجراءات إدارة البلاغات

- عرض تفاصيل البلاغ :اسم المبلِّغ، البلدية، الموقع، درجة الخطورة، والوصف
- تغيير حالة البلاغ :تحريكه من" قيد الانتظار "إلى" قيد المعالجة "ثم" تم الحل"
- تصفية البلاغات :حسب البلدية، الحالة، أو درجة الخطورة
- الإشعارات :تصل إشعارات تلقائية عند تقديم بلاغ جديد

نصيحة :يُنصح بمراجعة البلاغات ذات الخطورة العالية) الحمراء (أولاً لضمان سرعة الاستجابة الميدانية.

6.الإبلاغ عن نقطة سوداء

تتيح المنصة للمواطنين والمسؤولين تقديم بلاغات حول النقاط السوداء الجديدة أو المصبات العشوائية، مما يسهم في تعزيز المشاركة المجتمعية في عمليات النظافة.

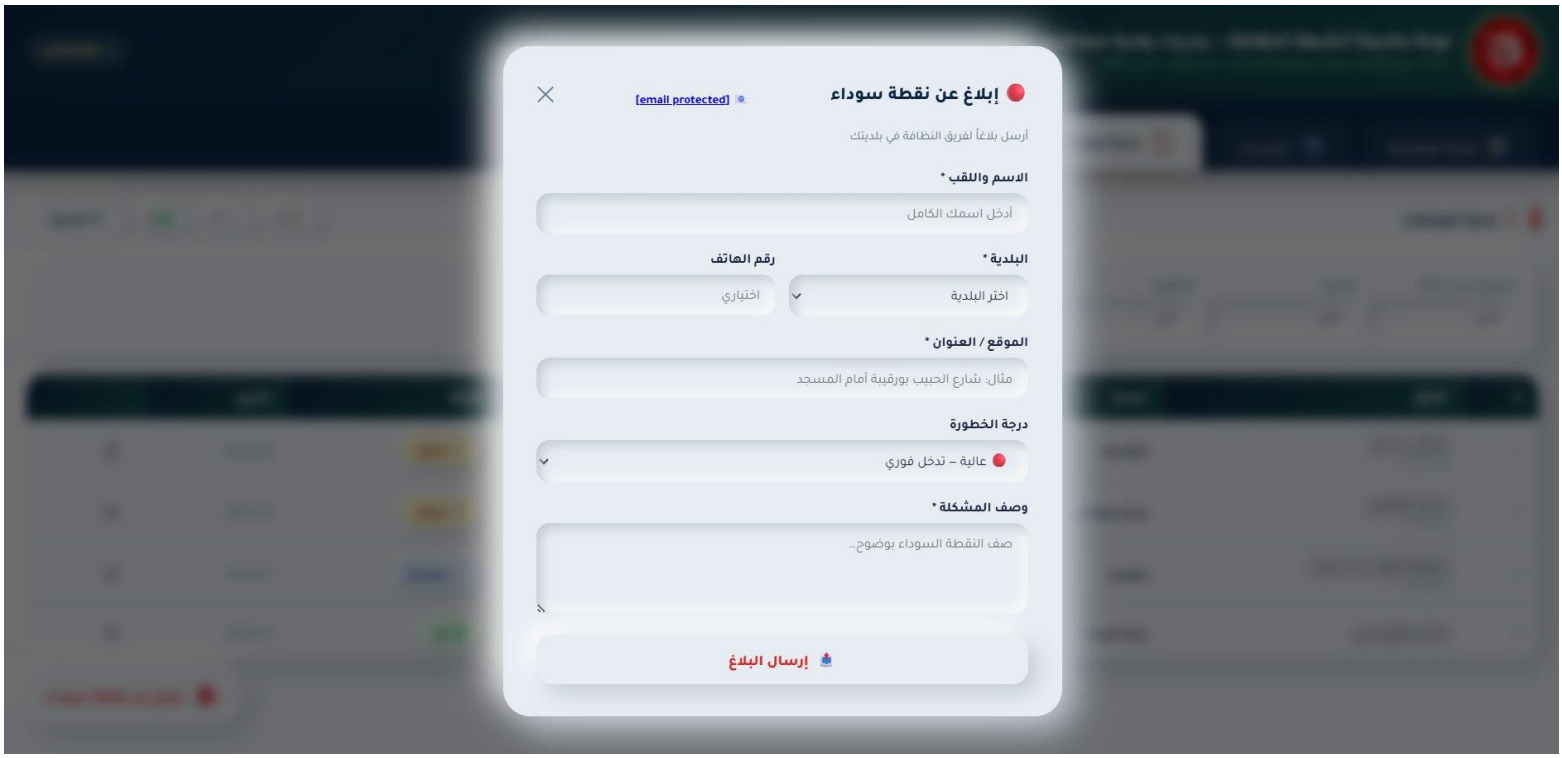

الشكل 4 – نموذج الإبلاغ عن نقطة سوداء

البلاغ تقديم خطوات

1. انقر على زر" إبلاغ عن نقطة سوداء "الظاهر في أعلى الشاشة أو في أسفلها
2. أدخل الاسم واللقب الكاملين في الحقل المخصص
3. اختر البلدية المعنية من القائمة المنسدلة
4. أدخل رقم الهاتف) اختياري، لتمكين التواصل معك(
5. حدد الموقع أو العنوان بدقة) مثال :شارع الحبيب بورقيبة أمام المسجد(
6. اختر درجة الخطورة المناسبة
7. اكتب وصفاً واضحاً للمشكلة في مربع النص
8. انقر على" إرسال البلاغ "لتأكيد تقديم البلاغ

الخطورة درجات

درجة الخطورة	الوصف	الاستجابة وقت
عالية – تدخل فوري	مصب ضخم أو نقطة تشكل خطراً صحياً مباشراً على السكان	24 ساعة خلال
متوسطة	تراكم نفايات كبير في منطقة سكنية أو تجارية	48-72 ساعة خلال
منخفضة	نقطة نفايات بسيطة لا تشكل خطراً فورياً	أسبوع خلال

7.الأسئلة الشائعة

? من يمكنه استخدام المنصة؟

المنصة مفتوحة للمواطنين لتقديم البلاغات .أما الوصول الكامل لإدارة البلاغات وعرض التقارير فهو مخصص للمسؤولين والموظفين المعيَّنين في الولاية والبلديات.

? كيف يمكنني معرفة أن بلاغي وصل؟

عند إرسال البلاغ بنجاح تظهر رسالة تأكيد على الشاشة .يمكن أيضاً تتبع حالة البلاغ عبر قسم "إدارة البلاغات "من طرف المسؤولين.

? ما هو الفرق بين" النقطة السوداء "و"المصب العشوائي"؟

النقطة السوداء :موقع يتراكم فيه النفايات بشكل متكرر وغير رسمي .المصب العشوائي :موقع يُستخدم كمكب نفايات غير قانوني بكميات كبيرة وقد يشكل خطراً بيئياً وصحياً.

? هل يمكنني الإبلاغ عن نقطة خارج بلديتي؟

نعم، يمكنك اختيار أي بلدية من قائمة البلديات الـ 23 المتوفرة في النموذج.

? ما الذي يعني مصطلح "KPIs" في لوحة المتابعة؟

KPIsهي اختصار لـ Key Performance Indicators أي" مؤشرات الأداء الرئيسية"، وهي الأرقام الكبيرة الظاهرة في الشاشة الرئيسية التي تعطي نظرة سريعة عن الوضع العام.

? من أجد مساعدة تقنية؟

للتواصل مع فريق التطوير يمكنك مراسلتهم عبر البريد الإلكتروني الظاهر في نموذج البلاغات، أو التواصل مع الكاتب العام لولاية صفاقس.

هذا الدليل أُعد لتيسير استخدام منصة متابعة النظافة لدى جميع المعنيين.

لأي استفسار أو ملاحظة، يُرجى التواصل مع فريق العمل.

– 2026 ©ولاية صفاقس – جميع الحقوق محفوظة